Manual de Usuario: Tablero de Consulta de Estudios de la Biblioteca Virtual de Aguas Subterráneas (BiVAS)

Contenido

1. Introducción 2
2. Características Principales 2
3. Guía de Uso Paso a Paso 2
   3.1 Paso 1: Selección por Entidad Federativa 2
   3.2 Paso 2: Uso de Buscadores Específicos 3
   3.3 Paso 3: Interacción con la Tabla de Resultados 6
   3.4 Paso 4: Exportación y Limpieza de Filtros (limpiar selecciones) 7
4. Preguntas Frecuentes (FAQ) 9
5. Soporte Técnico y Contacto 9

1. Introducción

El Tablero de Consulta BiVAS es una herramienta digital diseñada para facilitar el acceso, búsqueda y descarga de estudios hidrogeológicos. Su interfaz moderna permite navegar entre cientos de registros de manera fluida y precisa.

2. Características Principales

- Filtros Multi-nivel: Permite segmentar la información por Estado y Acuífero de forma jerárquica.
- Búsqueda Semántica: Encuentra estudios por palabras clave contenidas en el título.
- Búsqueda Inteligente por ID: Localización instantánea de estudios específicos mediante un buscador animado que ahorra espacio en pantalla.
- Visualización Rápida: Acceso directo a carátulas y vistas previas de los documentos.
- Gestión de Tomos: Identificación clara de estudios que constan de múltiples volúmenes (Tomo 1, Tomo 2, etc.).
- Exportación de Datos: Capacidad de descargar los resultados filtrados directamente a formato Excel (CSV).

3. Guía de Uso Paso a Paso

3.1 Paso 1: Selección por Entidad Federativa

Utilice los menús desplegables superiores para delimitar su zona de interés.

Seleccione un *Estado* del primer filtro.

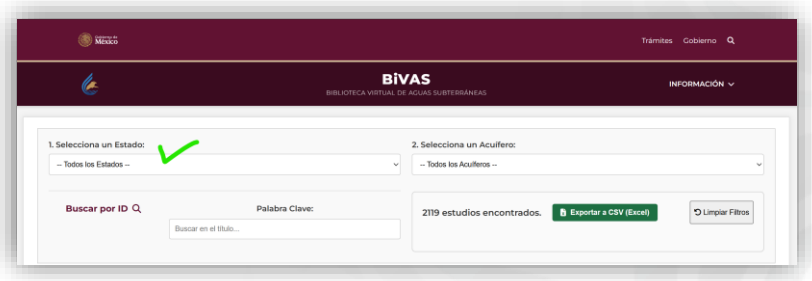

Figura 1. Filtro de Selección de Estados

El segundo listado (*Acuíferos*) se actualizará automáticamente para mostrar solo los Acuíferos pertenecientes a ese estado.

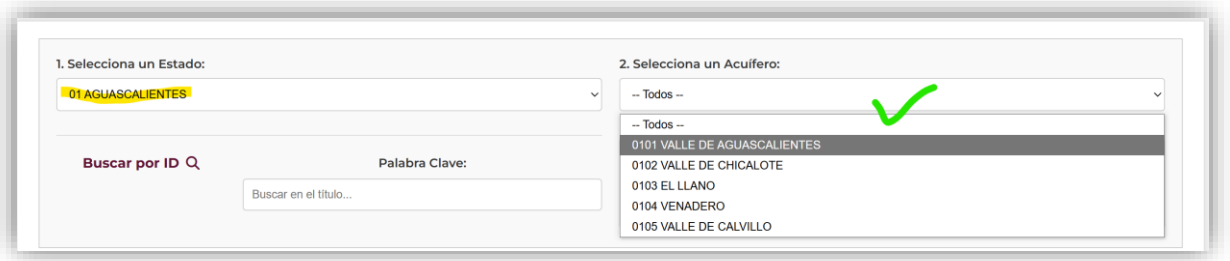

Figura 2. Selección de Acuífero

Tip: Si desea ver todos los estudios de un estado, deje el filtro de acuífero en "-- Todos --".

3.2 Paso 2: Uso de Buscadores Específicos

En la sección central encontrará dos herramientas potentes:

Palabra Clave: Escriba cualquier término relacionado con el tema del estudio para filtrar la tabla en tiempo real.

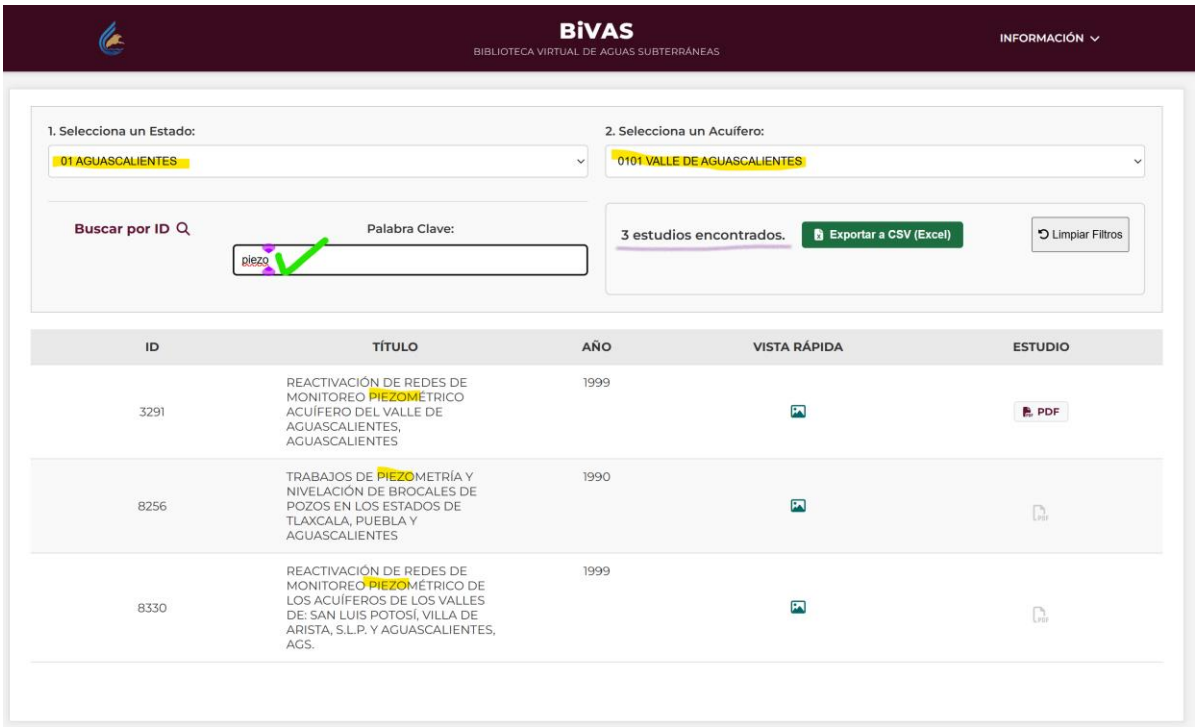

Figura 3. Buscador instantáneo por palabras clave

Buscador por ID: Haga clic en el icono de la lupa o en el texto "*Buscar por ID*". Se desplegará una caja de texto donde podrá escribir el número del estudio. Si borra el número, el buscador se contraerá automáticamente para limpiar la vista.

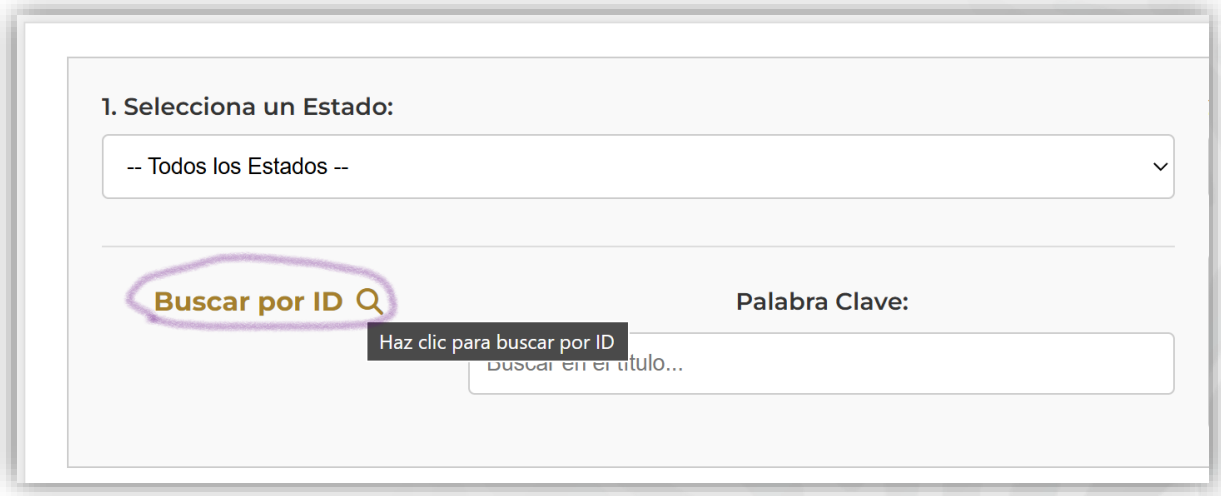

Figura 4. Filtro por ID del Estudio

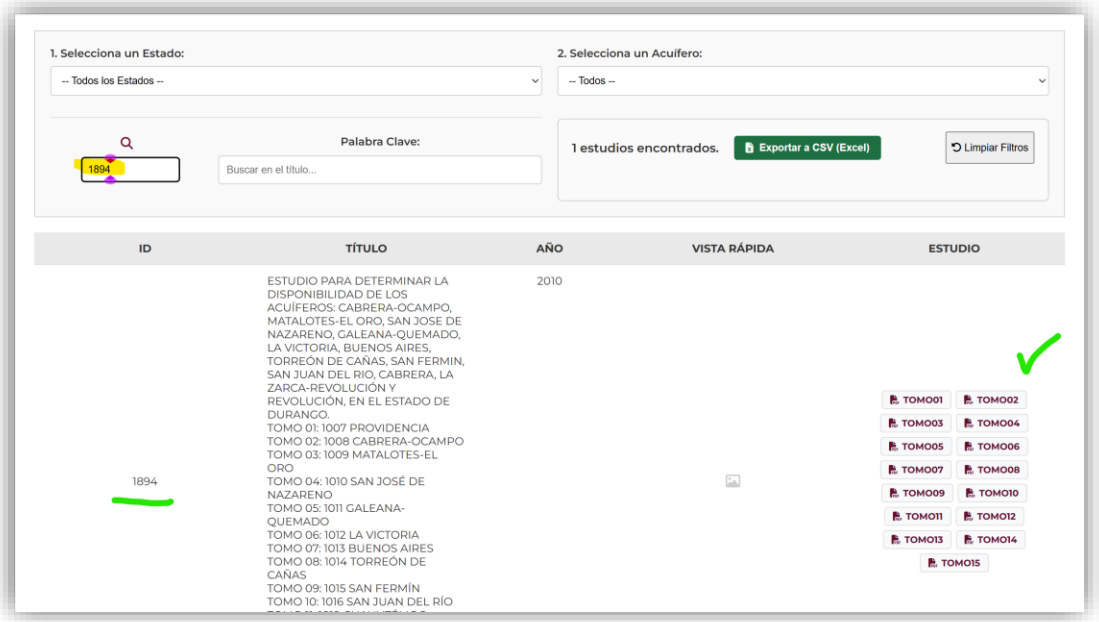

Figura 5. Si el ID coincide con algún registro del acervo de Estudios, se mostrará su información

3.3 Paso 3: Interacción con la Tabla de Resultados

La tabla muestra la información organizada en 5 columnas principales:

ID: Identificador único del estudio.

Título: Nombre oficial del documento.

Año: Fecha de publicación o elaboración.

Vista Rápida: Icono de imagen para ver la portada del estudio.

Estudio: Botones de PDF para abrir o descargar el documento.

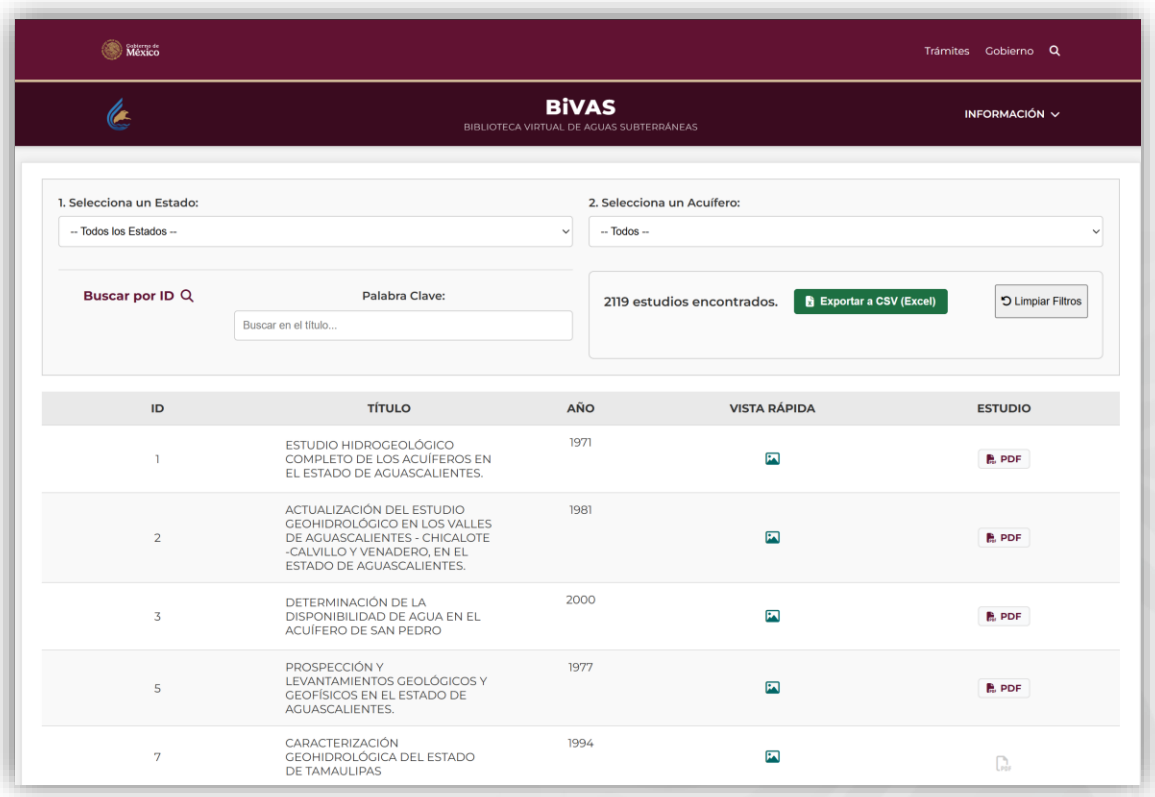

Figura 6. Los componentes de la Tabla de Resultados de la Búsqueda de Estudios.

3.4 Paso 4: Exportación y Limpieza de Filtros (limpiar selecciones)

Exportar a Excel: Una vez aplicados sus filtros, haga clic en el botón verde "*Exportar a CSV*" para guardar su búsqueda en su computadora.

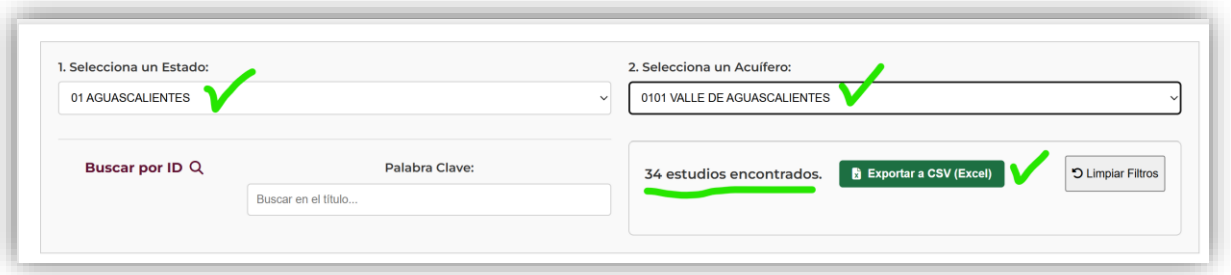

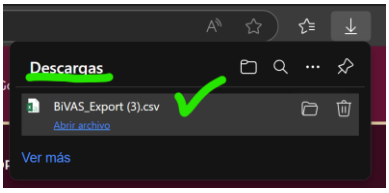

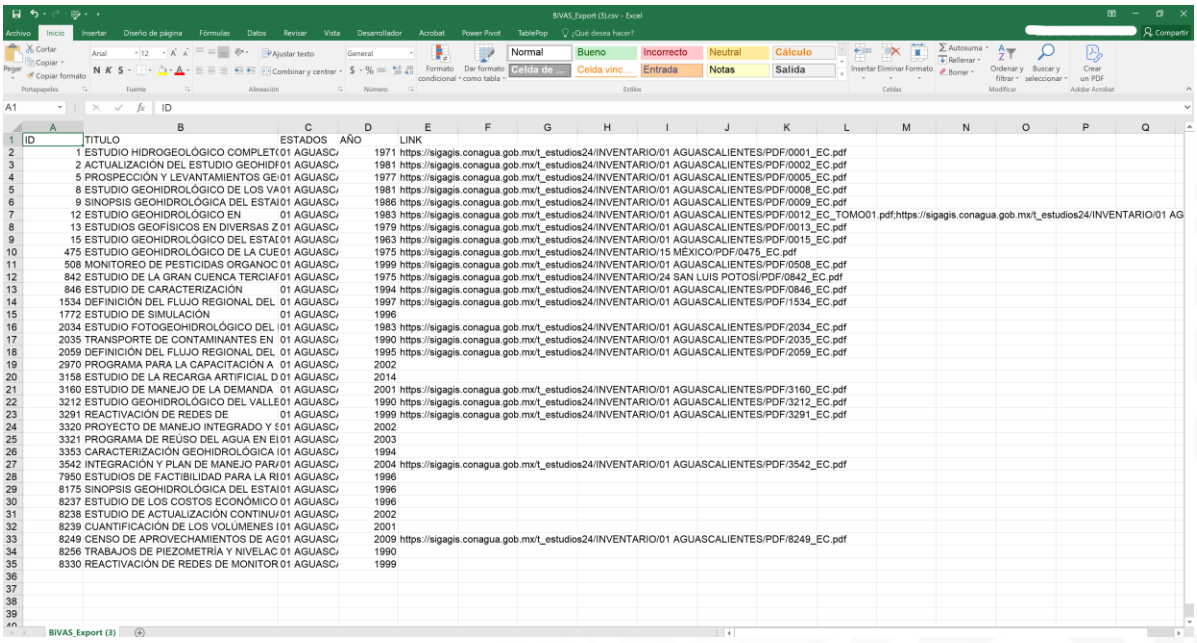

ID	TITULO	ESTADOS	AÑO	LINK
1	ESTUDIO HIDROGEOLÓGICO COMPLET	01 AGUASC	1971	https://sigagis.conagua.gob.mx/t_estudios24/INVENTARIO/01 AGUASCALIENTES/PDF/0001_EC.pdf
2	ACTUALIZACIÓN DEL ESTUDIO GEOHID	01 AGUASC	1981	https://sigagis.conagua.gob.mx/t_estudios24/INVENTARIO/01 AGUASCALIENTES/PDF/0002_EC.pdf
5	PROSPECCIÓN Y LEVANTAMIENTOS GE	01 AGUASC	1977	https://sigagis.conagua.gob.mx/t_estudios24/INVENTARIO/01 AGUASCALIENTES/PDF/0005_EC.pdf
8	ESTUDIO GEOHIDROLÓGICO DE LOS VA	01 AGUASC	1981	https://sigagis.conagua.gob.mx/t_estudios24/INVENTARIO/01 AGUASCALIENTES/PDF/0008_EC.pdf
9	SINOPSIS GEOHIDROLÓGICA DEL ESTA	01 AGUASC	1986	https://sigagis.conagua.gob.mx/t_estudios24/INVENTARIO/01 AGUASCALIENTES/PDF/0009_EC.pdf
12	ESTUDIO GEOHIDROLÓGICO EN	01 AGUASC	1983	https://sigagis.conagua.gob.mx/t_estudios24/INVENTARIO/01 AGUASCALIENTES/PDF/0012_EC_TOMO01.pdf;https://sigagis.conagua.gob.mx/t_estudios24/INVENTARIO/01 AG
13	ESTUDIOS GEOFÍSICOS EN DIVERSAS Z	01 AGUASC	1979	https://sigagis.conagua.gob.mx/t_estudios24/INVENTARIO/01 AGUASCALIENTES/PDF/0013_EC.pdf
15	ESTUDIO GEOHIDROLÓGICO DEL ESTA	01 AGUASC	1963	https://sigagis.conagua.gob.mx/t_estudios24/INVENTARIO/01 AGUASCALIENTES/PDF/0015_EC.pdf
475	ESTUDIO GEOHIDROLÓGICO DE LA CUE	01 AGUASC	1975	https://sigagis.conagua.gob.mx/t_estudios24/INVENTARIO/15 MÉXICO/PDF/0475_EC.pdf
508	MONITOREO DE PESTICIDAS ORGANOC	01 AGUASC	1999	https://sigagis.conagua.gob.mx/t_estudios24/INVENTARIO/01 AGUASCALIENTES/PDF/0508_EC.pdf
842	ESTUDIO DE LA GRAN CUENCA TERCIAF	01 AGUASC	1975	https://sigagis.conagua.gob.mx/t_estudios24/INVENTARIO/24 SAN LUIS POTOSÍ/PDF/0842_EC.pdf
846	ESTUDIO DE CARACTERIZACIÓN	01 AGUASC	1994	https://sigagis.conagua.gob.mx/t_estudios24/INVENTARIO/01 AGUASCALIENTES/PDF/0846_EC.pdf
1534	DEFINICIÓN DEL FLUJO REGIONAL DEL	01 AGUASC	1997	https://sigagis.conagua.gob.mx/t_estudios24/INVENTARIO/01 AGUASCALIENTES/PDF/1534_EC.pdf
1772	ESTUDIO DE SIMULACIÓN	01 AGUASC	1996	
2034	ESTUDIO FOTOGEOHIDROLÓGICO DEL	01 AGUASC	1983	https://sigagis.conagua.gob.mx/t_estudios24/INVENTARIO/01 AGUASCALIENTES/PDF/2034_EC.pdf
2035	TRANSPORTE DE CONTAMINANTES EN	01 AGUASC	1990	https://sigagis.conagua.gob.mx/t_estudios24/INVENTARIO/01 AGUASCALIENTES/PDF/2035_EC.pdf
2059	DEFINICIÓN DEL FLUJO REGIONAL DEL	01 AGUASC	1995	https://sigagis.conagua.gob.mx/t_estudios24/INVENTARIO/01 AGUASCALIENTES/PDF/2059_EC.pdf
2970	PROGRAMA PARA LA CAPACITACIÓN A	01 AGUASC	2002	
3158	ESTUDIO DE LA RECARGA ARTIFICIAL D	01 AGUASC	2014	
3160	ESTUDIO DE MANEJO DE LA DEMANDA	01 AGUASC	2001	https://sigagis.conagua.gob.mx/t_estudios24/INVENTARIO/01 AGUASCALIENTES/PDF/3160_EC.pdf
3212	ESTUDIO GEOHIDROLÓGICO DEL VALLE	01 AGUASC	1990	https://sigagis.conagua.gob.mx/t_estudios24/INVENTARIO/01 AGUASCALIENTES/PDF/3212_EC.pdf
3291	REACTIVACIÓN DE REDES DE	01 AGUASC	1999	https://sigagis.conagua.gob.mx/t_estudios24/INVENTARIO/01 AGUASCALIENTES/PDF/3291_EC.pdf
3320	PROYECTO DE MANEJO INTEGRADO Y S	01 AGUASC	2002	
3321	PROGRAMA DE REÚSO DEL AGUA EN EL	01 AGUASC	2003	
3353	CARACTERIZACIÓN GEOHIDROLÓGICA I	01 AGUASC	1994	
3542	INTEGRACIÓN Y PLAN DE MANEJO PAR	01 AGUASC	2004	https://sigagis.conagua.gob.mx/t_estudios24/INVENTARIO/01 AGUASCALIENTES/PDF/3542_EC.pdf
7950	ESTUDIOS DE FACTIBILIDAD PARA LA R	01 AGUASC	1996	
8175	SINOPSIS GEOHIDROLÓGICA DEL ESTA	01 AGUASC	1996	
8237	ESTUDIO DE LOS COSTOS ECONÓMICO	01 AGUASC	1996	
8238	ESTUDIO DE ACTUALIZACIÓN CONTINU	01 AGUASC	2002	
8239	CUANTIFICACIÓN DE LOS VOLÚMENES	01 AGUASC	2001	
8249	CENSO DE APROVECHAMIENTOS DE AG	01 AGUASC	2009	https://sigagis.conagua.gob.mx/t_estudios24/INVENTARIO/01 AGUASCALIENTES/PDF/8249_EC.pdf
8256	TRABAJOS DE PIEZOMETRÍA Y NIVELAC	01 AGUASC	1990	
8330	REACTIVACIÓN DE REDES DE MONITOR	01 AGUASC	1999	

Figura 7. Botón de Exportar a formato CSV. Al dar clic se descargará el archivo CSV con los Estudios mostrados en pantalla y se puede abrir en el software Excel o cualquier otro editor de este tipo de archivos.

Limpiar Filtros: Si desea iniciar una nueva búsqueda desde cero, presione "*Limpiar Filtros*" para restablecer todos los campos instantáneamente.

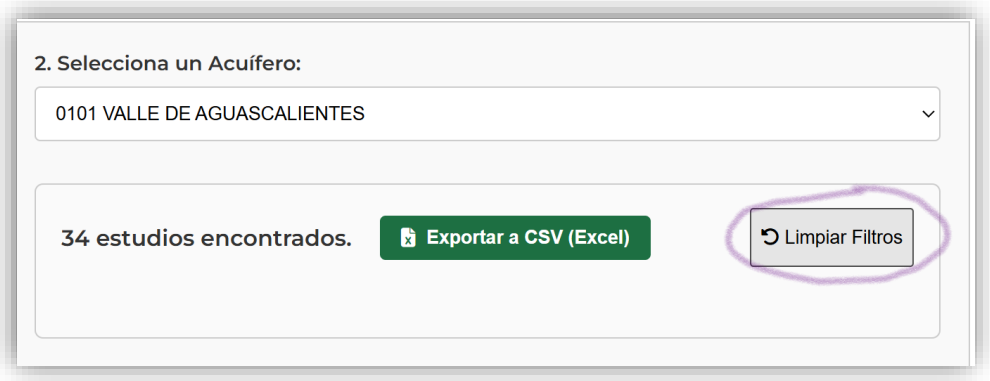

Figura 8. Botón Limpiar Filtros (limpia todas las selecciones para reanudar la búsqueda).

4. Preguntas Frecuentes (FAQ)

¿Por qué no aparece el botón de PDF en algunos estudios?
Si visualiza un icono de PDF en color gris, significa que el archivo digital se encuentra actualmente en proceso de carga o mantenimiento.

¿Puedo buscar varios ID a la vez?
El buscador por ID está diseñado para localizaciones precisas de un solo registro. Para búsquedas generales, utilice el campo de "Palabra Clave".

¿Cómo consulto un estudio físicamente?
Puede hacer clic en la opción "Acerca de" en el menú superior para ver la dirección física de la biblioteca y los requisitos de acceso.

5. Soporte Técnico y Contacto

Si presenta problemas técnicos con el Tablero o requiere asistencia con la información del acervo, ponemos a su disposición los siguientes medios:

Correo Electrónico Principal: biblioteca_sgt_gas@conagua.gob.mx
Asunto: Favor de iniciar el asunto del correo como [Soporte BiVAS] para una atención más ágil.
Consulta Presencial: Avenida Insurgentes Sur No. 2416, planta baja, Colonia Copilco El Bajo, Alcaldía Coyoacán, CDMX.

Horario de Atención: Lunes a Viernes de 9:00 a 18:00 hrs (Previa cita).